TRIPS & ROADS

Trips&Roads

Aperçu du site

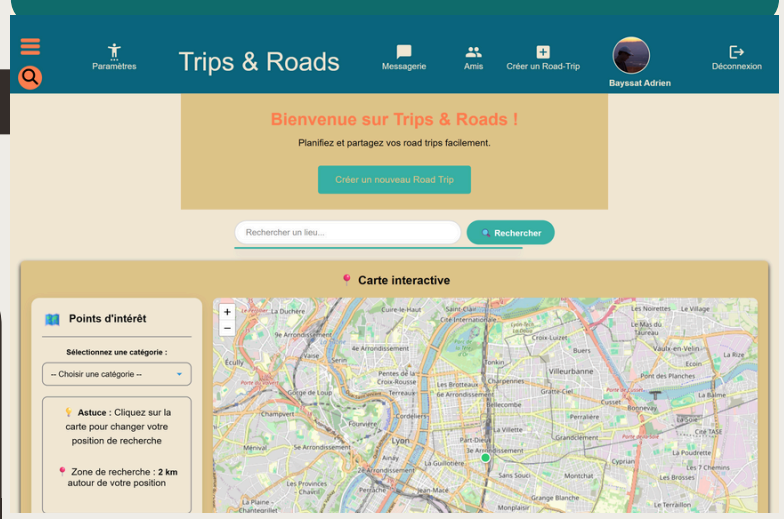

Objectifs

- ✓ Planifier des road-trips facilement
- ✓ Créer des itinéraires personnalisés
- ✓ Visualiser les trajets avec OSM
- ✓ Partager ses voyages avec une communauté

Acteurs

Développeurs :
BULLE Céleste
LAMBERT Sasha
PONCET Lenny
BAYSSAT Adrien
Tuteur :
BOUTIN Jean-Pierre

IUT Lyon 1
l'excellence technologique

Architecture

PHP <?>

Base de données (MariaDB)

Site Web (HTML/CSS/JS)

Le site repose sur une architecture web classique reliant interface utilisateur, serveur php, base de données et OpenStreetMap

{.js}

JavaScript

Librairies (OpenStreetMap)

Fonctionnalités

- Gestion de profil (données, photo, confidentialité)
- Carte du monde interactive
- Creation de Road Trip
- Avis & Commentaire
- Ajout d'amis & messagerie
- Partage de Road Trip
- Accessible au personne ayant une déficience visuelle

Technologies

HTML5 JS CSS3 php MariaDB

Intégration OpenStreetMap

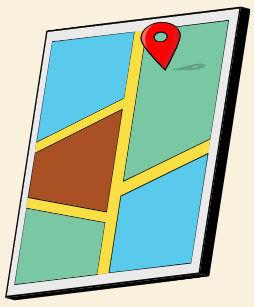

- Carte interactive
- Données dynamiques
- Utilisation de librairies

Aperçu du site

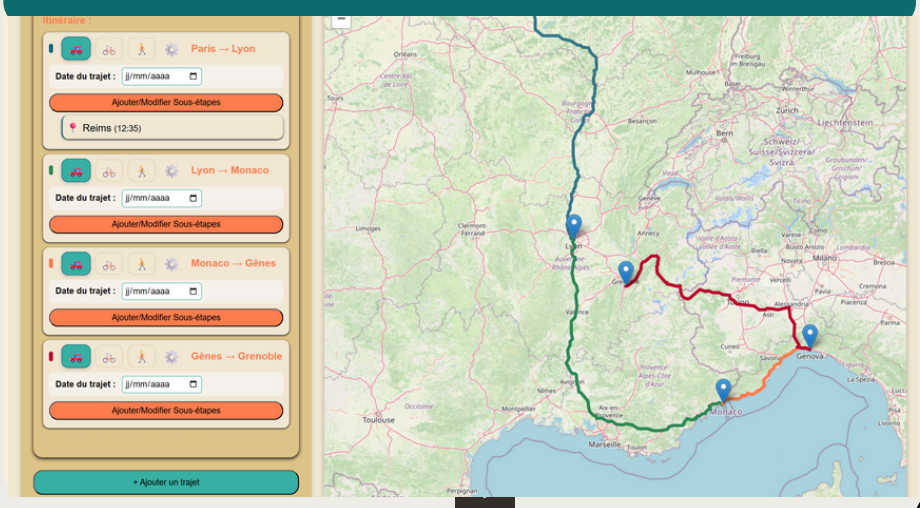

Trips & roads en chiffre

- En moyenne le temps pour créé un road trip clair est divisé par 2 !
- +10 000 lignes de code
- +150h/personnes soit 450h au total